Dispensansökan från generellt biotopskydd

1 Administrativa uppgifter

1.1 Sökanden

Företag: Ljungby kommun

Organisationsnummer: 212000-0670

Adress: Olofsgatan 9, 341 83 Ljungby

Telefon: 0372-78 93 02

Mejl: jakob.ruter@ljungby.se

Projektledare: Jakob Ruter

Kontaktperson: Jakob Ruter

1.2 Berörda fastigheter

Fastighetsbeteckning: Fastighetsbeteckning/ar: Eka 3:3 och 3:6. Fastighetsbeteckningarna kommer att ändras eftersom fastighetsbildning pågår för avstyckning av kvarteren inom detaljplaneområdet.

Markägare: Ljungby kommun

Markägaren är samma som sökanden/Markägaren är inte samma som sökanden: Ja

Markägaren har godkänt åtgärden? Ja

Finns innehavare för servitut på fastigheten? På fastigheterna finns flera rättigheter, när den nya fastighetsbildningen är klar kommer ett servitut finnas för kommunen för att ta sig igenom kvartersmarken.

2 Beskrivning av biotop

2.1 Typ av biotop

Generellt biotopskydd - odlingsröse.

3 Syfte med planerad åtgärd och omfattning

Syftet med åtgärden i Ekalunds verksamhetsområde är att genom upplösning av biotopskydd möjliggöra en utveckling av området till industri och verksamhetsmark. Totalt omfattar ansökan upplösning av det generella biotopskyddet för 12 odlingsrösen.

Planen för området är att skapa ett nytt område för olika typ av verksamheter tillsammans med drivmedelsstation, restaurang och annan service samt ett område för tekniska anläggningar.

Enligt detaljplanen för områden finns mellan den planerade kvartersmarken och allmän platsmark mark planlagd som "NATUR". Dessa områden ska vara gröna områden med cykelvägar och utplacerade sittplatser, som möjliggör att de kan användas som rekreationsområden. Kommunens avsikt är därför att flytta stenarna från de odlingsrösen som ligger inom kvartersmark till de område som planlagts som "Natur" (se bilaga 4)

Totalt berörs 12 av områdets 24 odlingsrösen.

4 Särskilda skäl

Särskilda skäl är att exploatering av området är av stort allmänintresse. I Ljungbys översiktsplan från 2020, antagen i januari 2022 är berört område utpekat för utveckling till verksamheter och industri. I dagsläget finns ingen planlagd mark utmed E4:an i Ljungby och efterfrågan är stor.

I en utredning "Inventering av nya områden för bostäder och industri i Ljungby stad" från 2008 har konstaterats att området som numera kallas Ekalunds verksamhetsområde anses som lämpligt för en utbyggnad. Det attraktiva läget vid E4:an tillsammans med goda geotekniska förhållanden, större avstånd till bostäder och begränsade naturvärden är fördelar som anges i inventeringen.

5 Beskrivning av biotopen

Ekalunds verksamhetsområde består av ett ca 80 hektar stort område, beläget väster om E4 och norr om Ekaindustriområde vid trafikplats Ljungby Norra (se bilaga 1). Området har haft en lång kulturhistorisk kontinuitet, vilket den fossilåkermarken, boplatser och stensättningar vittnar om. De arkeologiska utredningarna som gjorts i samband med planläggning av området visar på mänsklig aktivitet i området redan under stenåldern och att människor troligen har varit bofasta i området sedan vikingatiden.

Inom området har det tidigare legat tre gårdar med relativt öppen mark runt inägorna. Gårdarna finns idag inte kvar men avgränsningarna efter tomterna går fortfarande att läsa i landskapet. Bland annat genom tomtgränser, åkrar, odlingsrösen, stenmur och fägatan som skiljt inägomark mot utmark. Stora delar av åkermarken har idag lämnats för igenväxning. I den södra delen av området brukas fortfarande åkrarna för vallodling. En del av den tidigare åkermarken som lämnats för igenväxning används idag som endurobana. De norra delarna av området består av barrskogsdominerad skogsmark.

I det 80 hektar stora planområdet området finns totalt 24st odlingsrösen, belägna i områdets södra del i anslutning till jordbruksmarken (se bilaga 2).

Den här ansökan avser 12 av områdets totalt 24 odlingsrösen, (se bilaga 2). Röse; 1,2, 3, 4, 5, 6, 7, 19, 20, 21, 22 och 24, är odlingsrösena som ansökan avser.

Den största koncentrationen av odlingsrösen finns vid områdets högsta punkt på en ås i den södra delen av området. Vid åsen finns också områdets högsta naturvärden med flera gamla ekar. Enligt detaljplanen kommer naturen på åsen och dess odlingsrösen att bevaras som natur.

Flera av de rösen som berörs hyser relativt låga biologiska värden då de ligger på sidan av åkermarken som till stora delar är igenväxt och beskuggat av träd, buskar eller sly (se bilaga 5).

Beskrivningen av biotopen är baserad på hur området såg ut under inventering av biotopskydden, juni 2022. Sedan inventeringen genomfördes har det börjat avverkas. Så beskrivningen av biotoperna kan skilja mot hur området ser ut idag.

6 Kompensationsåtgärder

För att minska den negativa påverkan som åtgärden innebär på biotoperna kommer stenarna från de rösen som behöver tas bort flyttas och placeras i ett soligt läge i utkanten av en ekdunge i områdets mitt, se (bilaga 4). Här kommer stenarna att placeras i ett större samlat röse i söderläge. I den södra delen av dungen växer idag ek, tall, hassel, en och rönn. I fältskiktet växer liljekonvalj, vitsippa och bredbladigt gräs. Miljön är stenig och längs utkanten av dungen finns flera av områdets äldre odlingsrösen. Dungen angränsar i söder och väster mot åkermark, i öster mot den gamla byvägen, i norr mot en gårdstomt där en av områdets tidigare gårdar varit belägna. Området dit stenarna flyttas kommer att bevaras som "Natur" enligt planen och tillgängliggöras för allmänheten, via en gång- och cykelväg.

För att motverka förlusten av den kulturhistoriska läsbarheten i landskapet kommer skyltar att placeras ut vid kulturlämningar, exempel kommer en skylt placeras vid fägatan som berättar om funktionen av en fägatan och om gårdarna som tidigare legat på platsen. Även vid den största koncentrationen av odlingsrösen sit stenarna flyttas kommer en skylt placeras ut. Skylten kommer att ha en förklarande text som berättar om odlingsrösens tidigare funktion samt om dess biologiska värde.

För att öka odlingsrösenas biologiska värde i området kommer sly runt rösen röjas undan med några års mellanrum. Ekar, samt bärande träd och buskar kommer att sparas. Ansvaret för förvaltning ligger på Ljungby kommun, tekniska förvaltningen, parkavdelningen.

7 Tidpunkt

Arbetet med stenarna kommer att utföras under augusti och september månad, från år 2023–2026.

8 Övriga upplysningar

Bilaga 1. Översiktskarta över området Ekalund

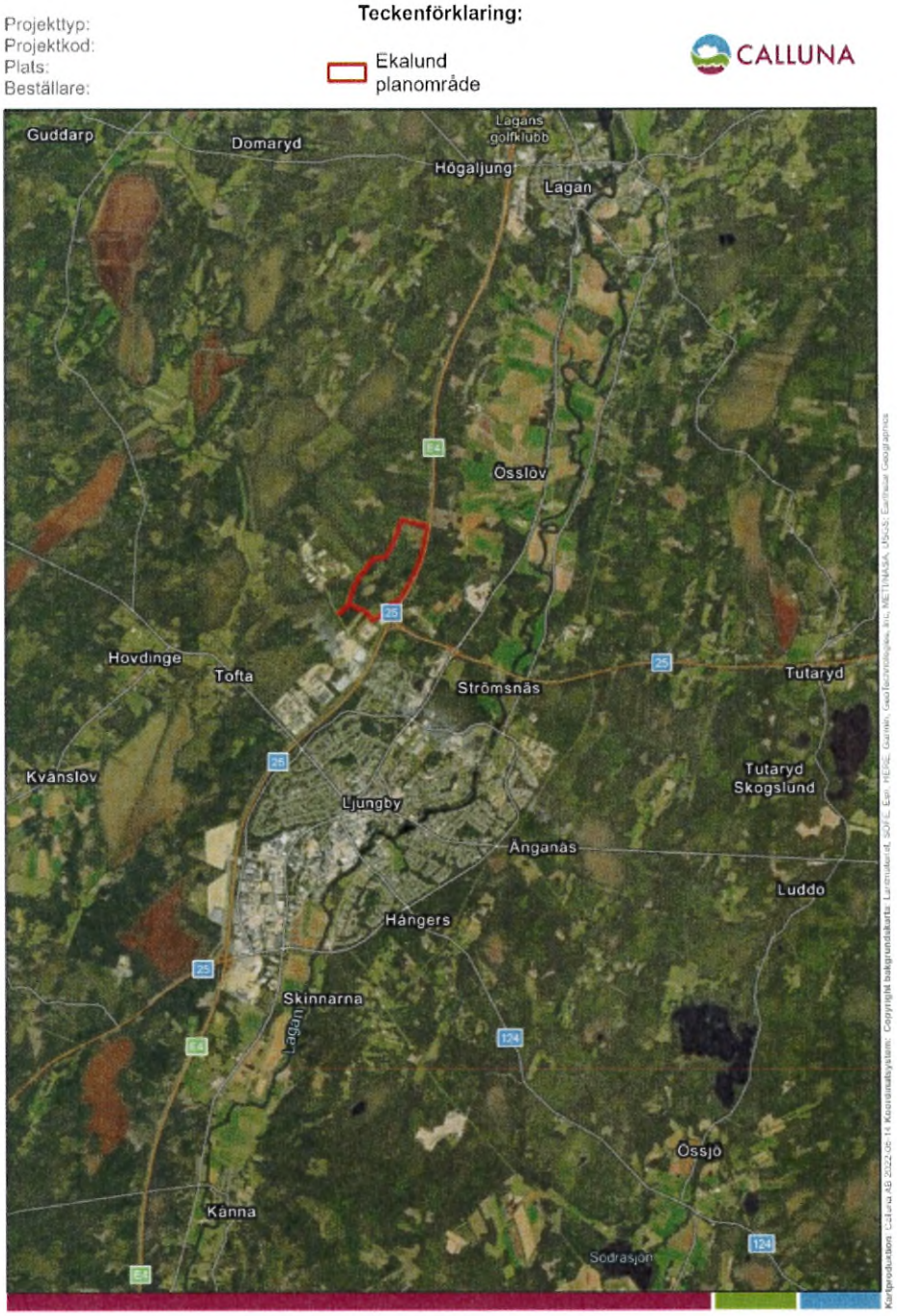

Figur 1. Översiktskarta över området eka.

Bilaga 2. Detaljkarta som visar berörda odlingsrösens lokalisering.

CALLUNA

TECKENFÖRKLARING:

Odlingsrösen

Ekalund planområde

Figur 2. Kartan visar alla områdets odlingsrösen markerat med orange i kartan, de odlingsrösen som dispensansökan avser är nr: 1, 2, 3, 4, 5, 6, 7, 19, 20, 21, 22 och 24 i kartan.

Bilaga 3. Plankarta

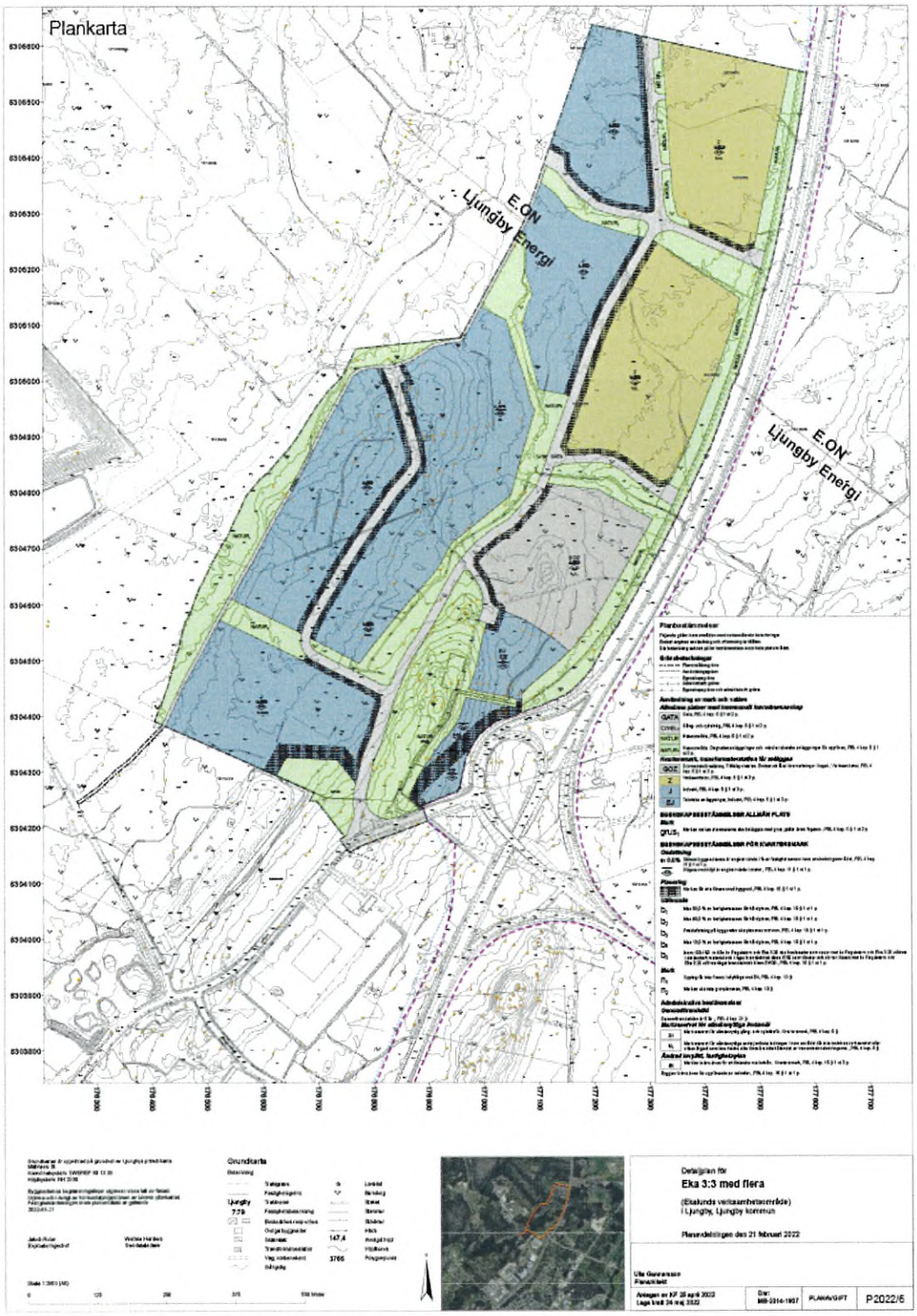

Figur 3. Plankarta över området.

Bilaga 4. Utsnitt ur plankartan, med utpekat läger för flytt av odlingsrösen.

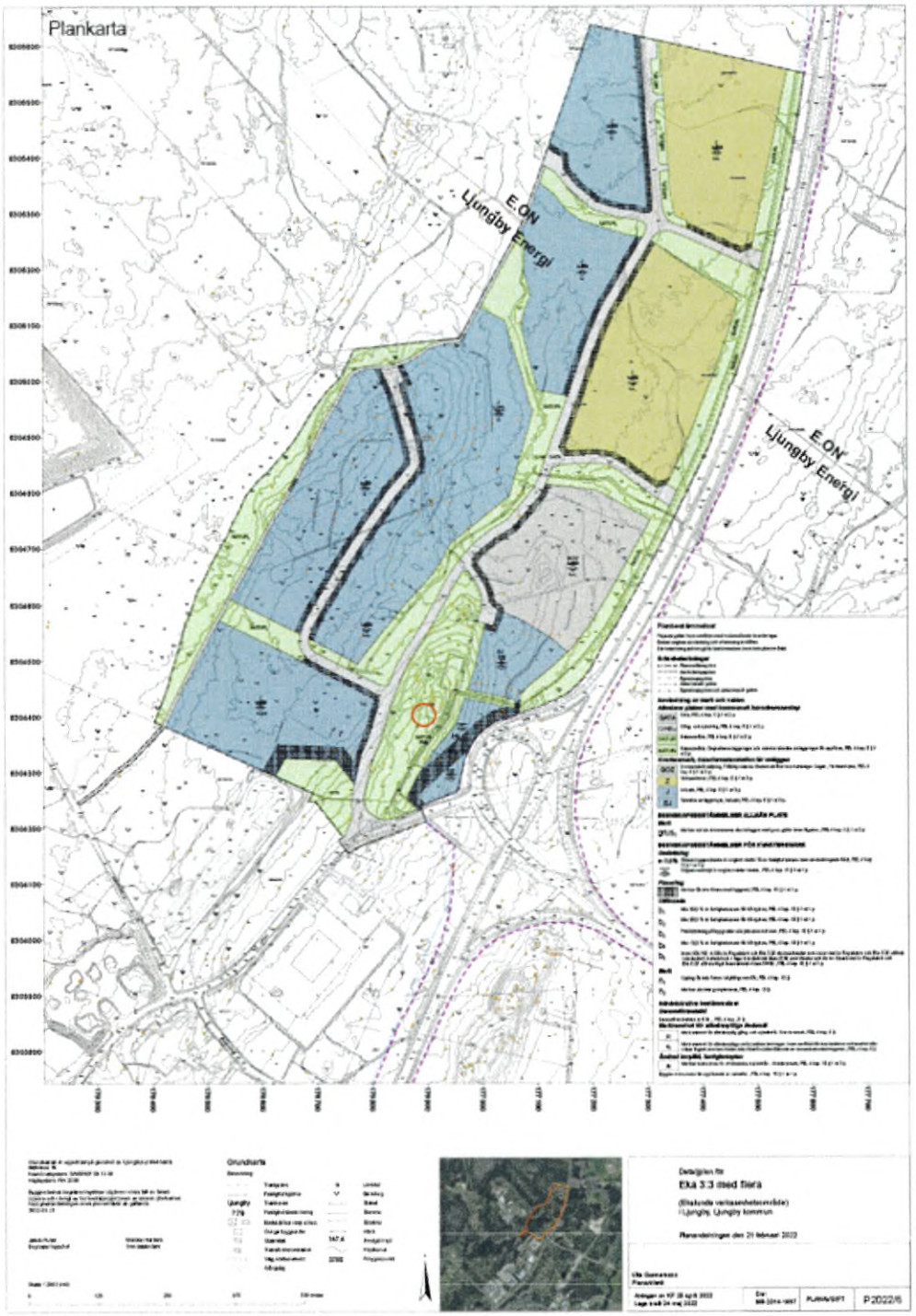

Figur 4. Plankarta med föreslaget läge för flytt av odlingsrösen, nytt läge markerat med röd cirkel i kartan.

Bilaga 5 – Attributdata och bilder

Tabell 5. Inmätta odlingsrösen med bilder.

ID	Typ av biotopskydd	Beskrivning	Överlappar med kvartersmark %
1	Odlingsröse i jordbruksmark	Odlingsröse beläget i angränsning till jordbruksmark, och barrskog. Röset består av flera större stenar. Igenväxning av asp, till viss del beskuggat.	100%

2	Odlingsröse i jordbruksmark	Odlingsröse beläget i angränsning till jordbruksmark, och barrskog. Stenröse med flera större stenar. Vill viss del beskuggat av omkring liggande barrskog.	100%

3	Odlingsröse i jordbruksmark	Odlingsröse i jordbruksmark. Beläget vid åkerkant. Stenröse med flera större stenar. Till liten del igenväxt och delvis övertäckt med ris.	100%

4	Odlingsröse i jordbruksmark	Odlingsröse i jordbruksmark. Angränsar till åkermark. Större stensamling. Delvis beskuggat av död ved och ek.	100%

5	Odlingsröse i jordbruksmark	Odlingsröse i jordbruksmark. Till stor del beskuggat och igenväxt med slyskog. Kan vara del av tidigare stenmur som plöjts/vuxit igen.	100%

6	Odlingsröse i jordbruksmark	Odlingsröse i jordbruksmark. Till stor del beskuggat och igenväxt med slyskog. Kan vara del av tidigare stenmur som plöjts/vuxit igen.	100%



7	Odlingsröse i jordbruksmark	Odlingsröse i jordbruksmark. Större odlingsröse med flera större stenar, beläget på åkermark/åkerholme. Till stor del beskuggat och bevuxet med sälg och björk.	65%

19	Odlingsröse i jordbruksmark	Odlingsröse i jordbruksmark. Röse med flera större stenar. Till stor del bevuxet och beskuggat av björk.	100%

20	Odlingsröse i jordbruksmark	Odlingsröse i jordbruksmark. Delvis bevuxet och beskuggat av björk och ek.	50%



21	Odlingsröse i jordbruksmark	Odlingsröse i jordbruksmark. Till stor del beskuggat av ek och hassel.	95%

22	Odlingsröse i jordbruksmark	Odlingsröse i jordbruksmark. Mindre röse beskuggat av ek.	100%

24	Odlingsröse i jordbruksmark	Odlingsröse beläget på tidigare jordbruksmark. Marken är lämnad för igenväxning och används idag som endurobana. Större röse som på ena sidan igenväxt och beskuggat med sly och björk.	100%